FERNANDO GISOLDI
ARCHITETTO

Via Remoto, 8 - Campoli Del Monte Taburno (BN)
fernando.gisoldi@archiworldpec.it
Http://ec2.it/architettofernandogisoldi
E-mail fgisol@tin.it

Studio di Progettazione

Tel./Fax 0824.873232 - Voip 0824.608864 - Cell. 338.8520810

Partita I.V.A. 00930750625 - Codice Fiscale GSL FNN 64B25 C250S

COMUNE

Campoli del Monte Taburno
(Provincia di Benevento)

PROGETTO

Modifica alla divisione interna, completamento e cambio di destinazione d'uso di un fabbricato sito alla c/da pantanelle

COMMITTENTE

DE SIMONE Salvatore

Allegato Unico	- Relazione tecnica - Stralci cartografici; - Grafici del P.C. 17/2006 - Grafici di progetto;

IL TECNICO
(Dott. Arch. Fernando Gisoldi)

ORDINE DEGLI ARCHITETTI - PIANIFICATORI - PAESAGGISTI E CONSERVATORI
FERNANDO GISOLDI
ARCHITETTO
N° 259
PROVINCIA DI BENEVENTO

FERNANDO GISOLDI
ARCHITETTO
E-mail fgisol@tin.it
Via Remoto, 6 - Tel/Fax 0824.873232
Studio di Progettazione Campoli Del Monte Taburno (BN)

COMUNE DI CAMPOLI DEL MONTE TABURNO
(Provincia di Benevento)

OGGETTO: **Modifica alla divisione interna, completamento e cambio di destinazione d'uso di un fabbricato sito alla c/da Pantanelle.**

COMMITTENTE: **De Simone Salvatore**

RELAZIONE TECNICA

Richiedente:

- De Simone Salvatore, nato a Campoli del Monte Taburno il 20/01/1966 (C.F. DSMSVT66A20B542I) ed ivi residente alla c/da Pantanelle snc in qualità di proprietario.

Con il presente progetto si prevede la **modifica alla divisione interna, completamento e cambio di destinazione d'uso di un fabbricato sito alla c/da Pantanelle** del Comune di Campoli M.T. (BN).

Tale fabbricato oggetto di intervento è attualmente destinato ad agriturismo. Con il presente progetto si chiede il cambio di destinazione d'uso da agriturismo ad abitazione.

L'immobile è riportato in catasto fabbricati al foglio n°1, p.lla n°769 del Comune di Campoli M.T.

Atti autorizzativi principali:

- Il presente fabbricato fu realizzato a seguito dell'approvazione della Commissione ex art. 14 Legge 219/81 nella seduta del 24/01/1987;
- Fu oggetto di cambio di destinazione d'uso da abitazione ad agriturismo, con Permesso di Costruire n°4 del 10/02/2005;
- Con Permesso di Costruire n°17 del 28/06/2006 furono autorizzati "*Lavori di adeguamento igienico funzionale di un agriturismo sito alla località Pantanelle del Comune di Campoli del Monte Taburno (BN)*".

Con il Permesso a Costruire n°17/2006 si prevedeva l'ampliamento del fabbricato, al piano terra, con volumi di progetto costituiti da un porticato, un ampliamento della cucina e un locale interrato da utilizzare come deposito.

In seguito al rilascio di tale Permesso a Costruire n°17/2006 furono realizzati il porticato e il volume interrato, mentre l'ampliamento della cucina non fu realizzato e il presente progetto costituisce anche variante in diminuzione di tale volume non realizzato.

Inoltre, si precisa, che per il volume interrato previsto con il P.C. 17/2006 e già realizzato (con pilastri diversamente posizionati dal progetto architettonico), non fu effettuato il preventivo deposito al genio civile, per cui resta a carico della ditta committente la richiesta di autorizzazione sismica in sanatoria, per la regolarizzazione dell'immobile e prima di procedere all'agibilità dei locali.

Con il presente progetto si prevede, oltre al cambio di destinazione d'uso, la modifica alla divisione interne dei locali cosi come riportato nei grafici di progetto allegati (inserimento di nuovi bagni ecc.).

C.F. GSLFNN64B25C250S - Cell. 338.8520810 – P. IVA 00930750625

L'intervento di progetto prevede anche lievi modifiche esterne;

- Considerato che l'immobile di che trattasi non è un bene vincolato ai sensi del Codice (Codice dei beni culturali e del paesaggio di cui al decreto legislativo 22 gennaio 2004, n. 42, e successive modificazioni), art. 136, comma 1, lettere a), b) e c) limitatamente, per quest'ultima, agli immobili di interesse storico-architettonico o storico-testimoniale, ivi compresa l'edilizia rurale tradizionale, isolati o ricompresi nei centri o nuclei storici;
- Considerato che tali modifiche sui prospetti sono eseguiti *nel rispetto delle caratteristiche architettoniche, morfotipologiche, dei materiali e delle finiture esistenti,*

Si ritiene che tali modifiche, rientrano tra gli **Interventi ed opere in aree vincolate esclusi dall'autorizzazione paesaggistica (allegato A di cui all'art. 2, comma 1)** del **D.P.R. n°31 del 13/02/2017**, per cui non è necessario acquisire il parere della competente Soprintendenza.

Inoltre nel volume interrato già realizzato, è previsto, nel presente progetto, la realizzazione di un bagno per disabili (attualmente, il fabbricato, viene utilizzato come struttura di accoglienza immigrati) con l'apertura di una porta esterna per l'accesso ad esso. Tale bagno per disabili con relativa porta di accesso, ai sensi dell'art. 79 del DPR 380/2001 s.m.i., può essere realizzato in deroga alle norme sulle distanze previste dai regolamenti edilizi e ciò consente l'apertura della porta esterna che normalmente non potrebbe essere realizzata in quanto il volume essendo interrato non rispetterebbe più le distanze prescritte.

Le caratteristiche dell'opera da realizzare; le facciate saranno tinteggiate con colori tenui, i canali di gronda e le pluviali in lamiera preverniciata in tinta rame.
L'intervento si inserisce coerentemente nel contesto ambientale senza generare alcun danno e in ogni caso la modifica allo stato dei luoghi resta compatibile con la tutela dell'ambiente prevista dalla normativa vigente per le modeste dimensioni dell'intervento.

VERIFICA DELLE CONFORMITA' ALLE PREVISIONI URBANISTICHE

Nel P.R.G. vigente l'area di progetto ricade in zona "E" agricola.
Nel P.T.P. vigente l'area di progetto ricade in zona "C.I.P.".
Per tale zona sono consentiti gli interventi previsti con i seguenti parametri urbanistici:
Non si prevede aumento di volumetria né di superficie utile.

ELABORATI COMPRESI NEL PRESENTE PROGETTO:

- Relazione tecnica;
- Inquadramento territoriale - scala 1:25000;
- planimetria catastale con l'indicazione dell'immobile oggetto dell'intervento scala 1:2000;
- Stralci cartografici;
- Elaborati grafici di cui al P.C. n°17 del 28/06/2006 - scala 1:100;
- Elaborati grafici di progetto - scala 1:100;

IL TECNICO
(Dott. Arch. Fernando GISOLDI)

ORDINE DEGLI ARCHITETTI - PIANIFICATORI - PAESAGGISTI E CONSERVATORI - PROVINCIA DI BENEVENTO
FERNANDO GISOLDI
ARCHITETTO
N° 259

C.F. GSLFNN64B25C250S - Cell. 338.8520810 – P. IVA 00930750625

INQUADRAMENTO TERRITORIALE
Comune di Campoli M.T.
scala 1:25000

immobile interessato alla trasformazione

Campoli
di Monte Taburno
Tocco Caudio
Pietà di Tocco
S. Michele
Fonte Pisciarello
Fonte Ingippo
Fonte Carrara
Fonte del Pero
Fonte Serra
Cava di pietra
Cava
Cava
Monaci
Carmine
M. Mauro
Mass. Frattaro
C. De Mizio
S. Pietro
Casino
Casino
Baracca
Mass. Punti
Mass. Lotoli
Mass. Costa la Fica
Cesco di Luccato
Cesco Mat
la Torre
Sorg. Acquariva
Sorg. Rivullo
Mass. Valle della Via
Mass. delle Grecce
Fonte la Croce
Fonte dei Mungilli
Fonte li Saudi
del Salice
Valle di Maio
Campopiano
Padula
Pezzillo
Chiesa
Gallura
Sperata
Cadavossolo
Costa Marina
Costa Marchese
Canaro Marchese
Nocella
Ripoli
Vigna
Cauto
Terra Dentra
Terra Cesa
Pandanello
Panicina
Canale Lungo
Rivullo
Cerrenoli
Comune
Sorbo
Mo
Mo
M

COMUNE DI CAMPOLI M.T.
Stalcio catastale F.01 p.lla 769

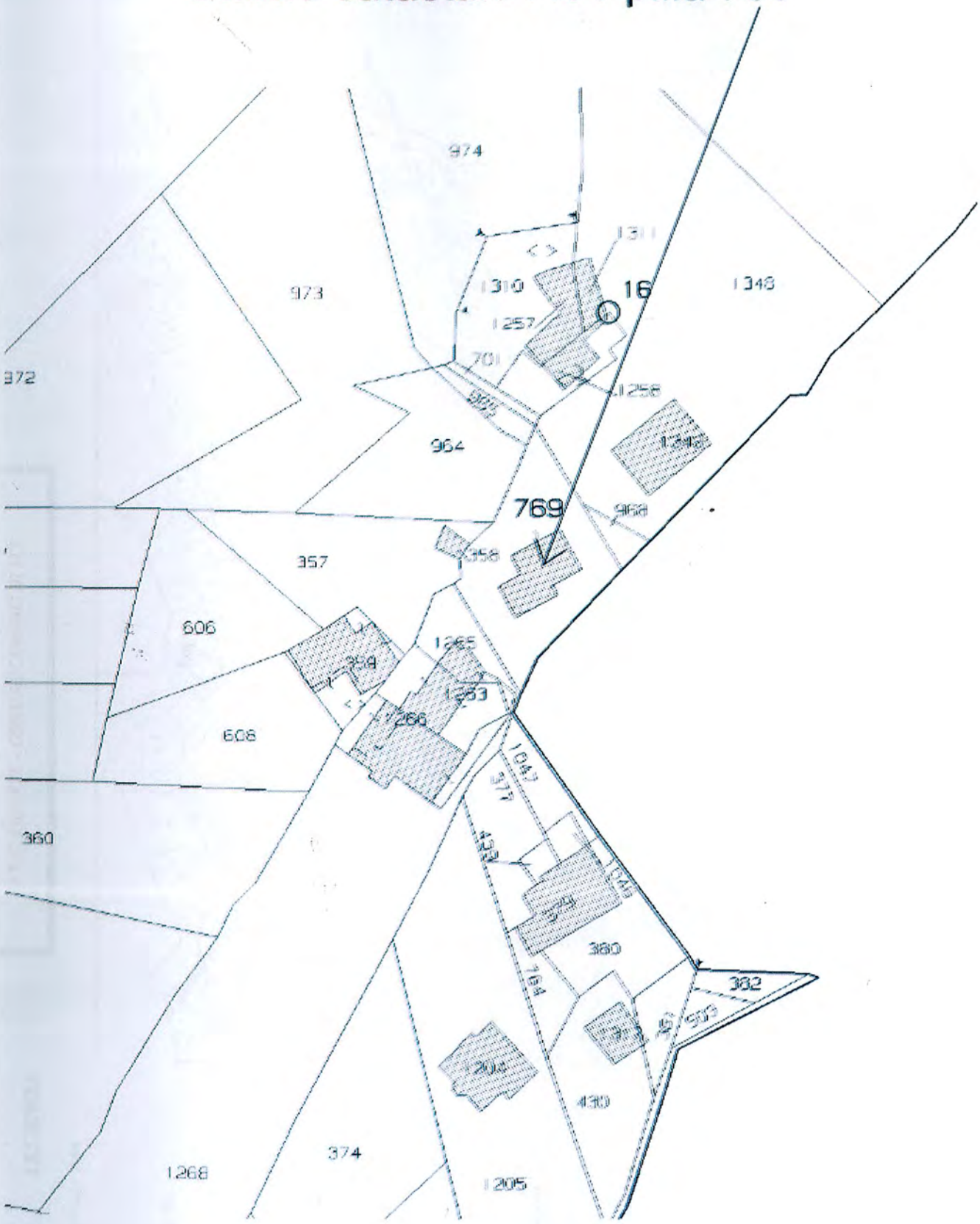

P.R.G. VIGENTE – COMUNE CAMPOLI DI M.T.

LEGENDA

- Limite zona R.U.A.- P.T.P.
- P.D.R
- ZONA "B"
- ZONA "C" ED. IND.
- ZONA "C"
- P E E P
- Zona "Ct" turistica
- Asilo – Scuole
- Camping
- Verde privato inedificabile
- Zona Cimiteriale
- Verde attrezzato pubblico
- Ospedale
- Parcheggio
- Attrezzature d'interesse generale
- Depuratore
- Area Sportiva
- Discarica
- Strada di progetto
- Zona per attrezzature religiose
- Zona di rispetto cimiteriale
- Zona di rispetto discarica depuratore
- Zona "D" artigianale

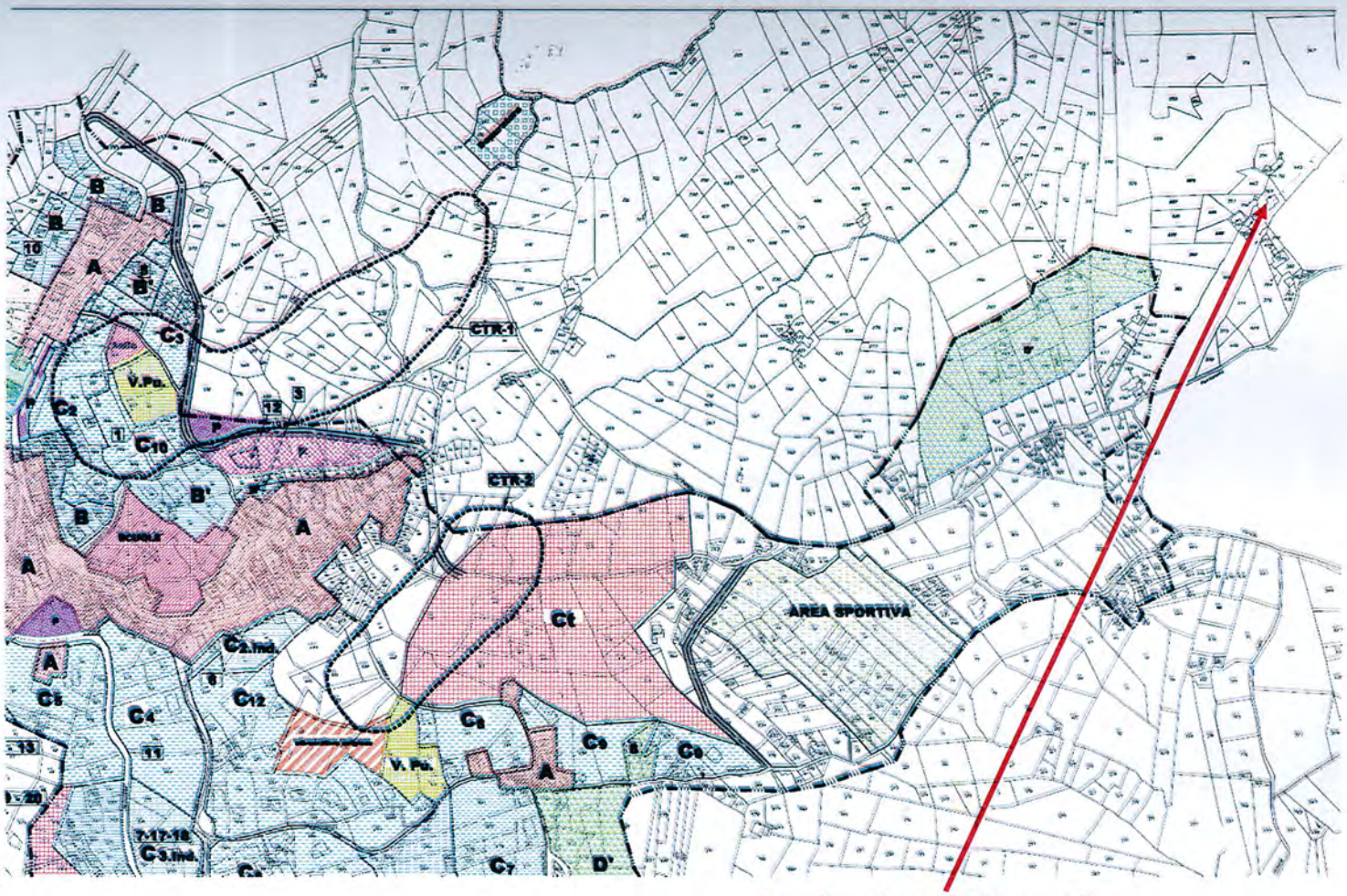

Localizzazione dell'immobile

Grafici di cui al P.C. n°17 del 28/06/2006 - scala 1:100

PIANO TERRA

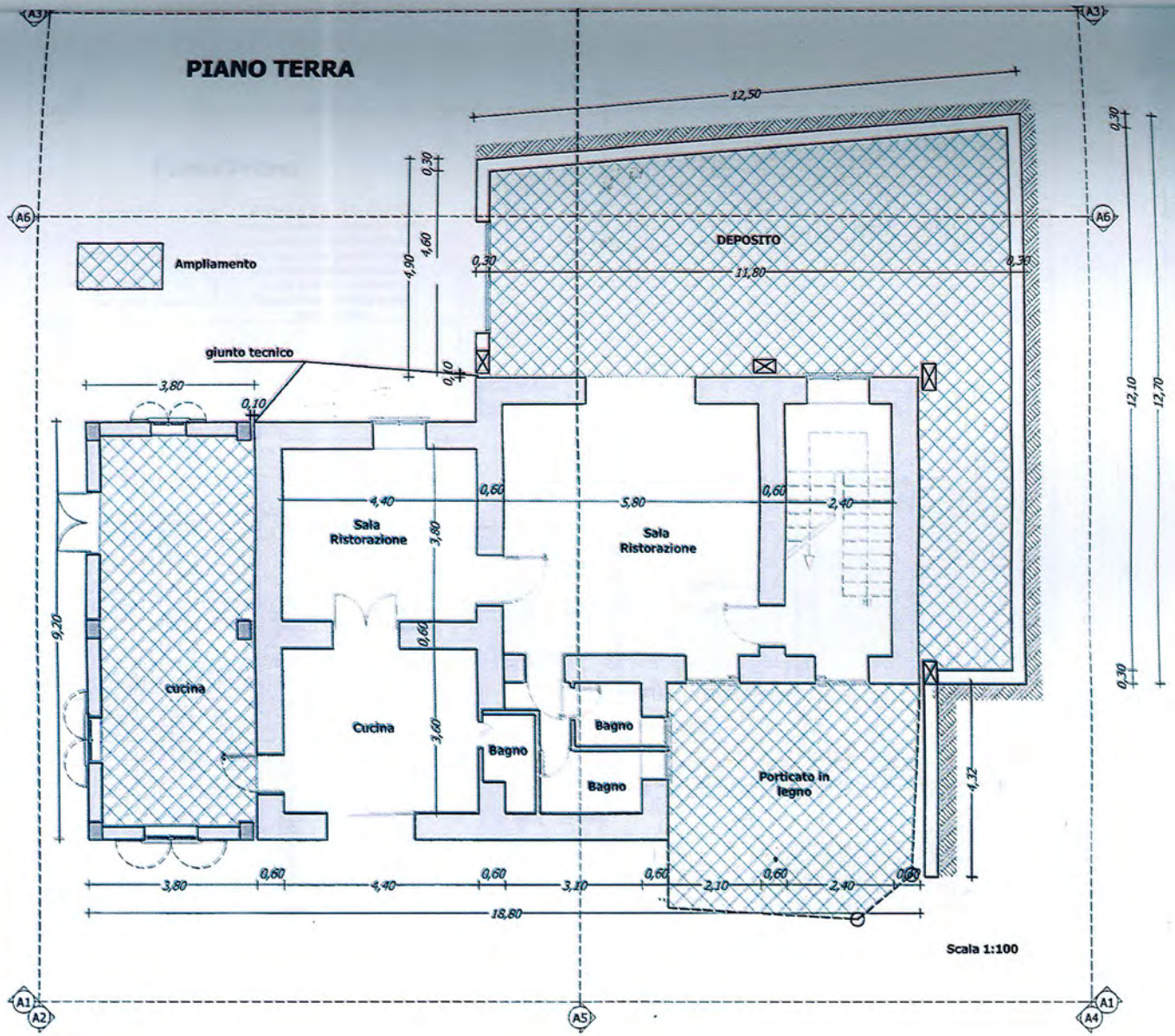
Ampliamento
giunto tecnico
DEPOSITO
Sala Ristorazione
Sala Ristorazione
cucina
Cucina
Bagno
Bagno
Bagno
Porticato in legno
12,50
11,80
0,30
0,30
0,30
0,30
4,90
4,60
0,10
0,10
3,80
4,40
0,60
5,80
0,60
2,40
3,80
9,20
0,60
3,60
12,10
12,70
4,32
3,80
0,60
4,40
0,60
3,10
0,60
2,10
0,60
2,40
0,60
18,80
A1
A2
A3
A4
A5
A6
Scala 1:100

Piano Primo

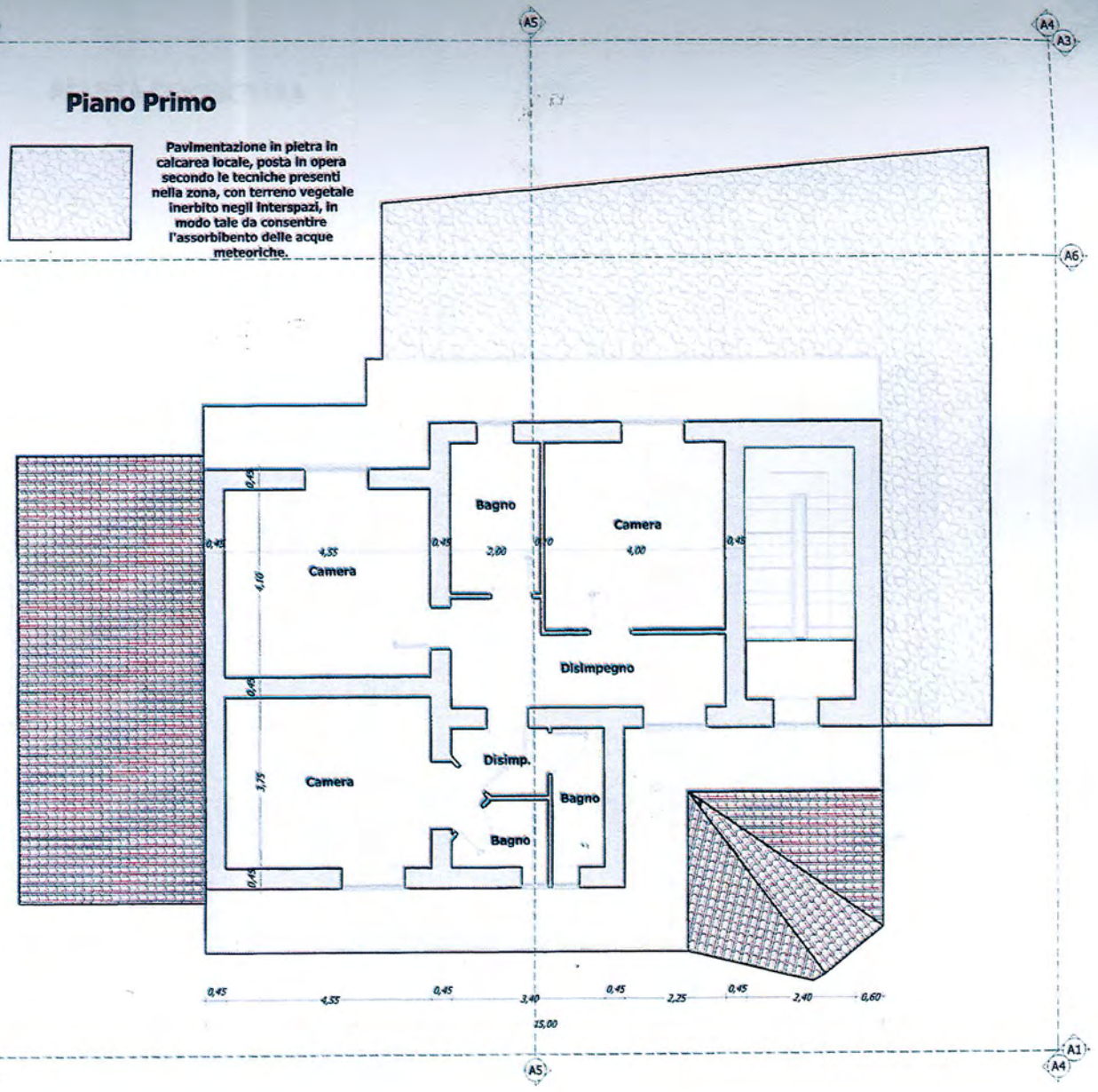
Pavimentazione in pietra in calcarea locale, posta in opera secondo le tecniche presenti nella zona, con terreno vegetale inerbito negli interspazi, in modo tale da consentire l'assorbibento delle acque meteoriche.
A1
A2
A3
A4
A5
A6
Camera
4,55
4,10
Bagno
2,00
Camera
4,00
Disimpegno
Camera
3,75
Disimp.
Bagno
Bagno
0,45
0,70
0,60
0,45
4,55
0,45
3,40
0,45
2,25
0,45
2,40
0,60
25,00

PIANTA COPERTURA

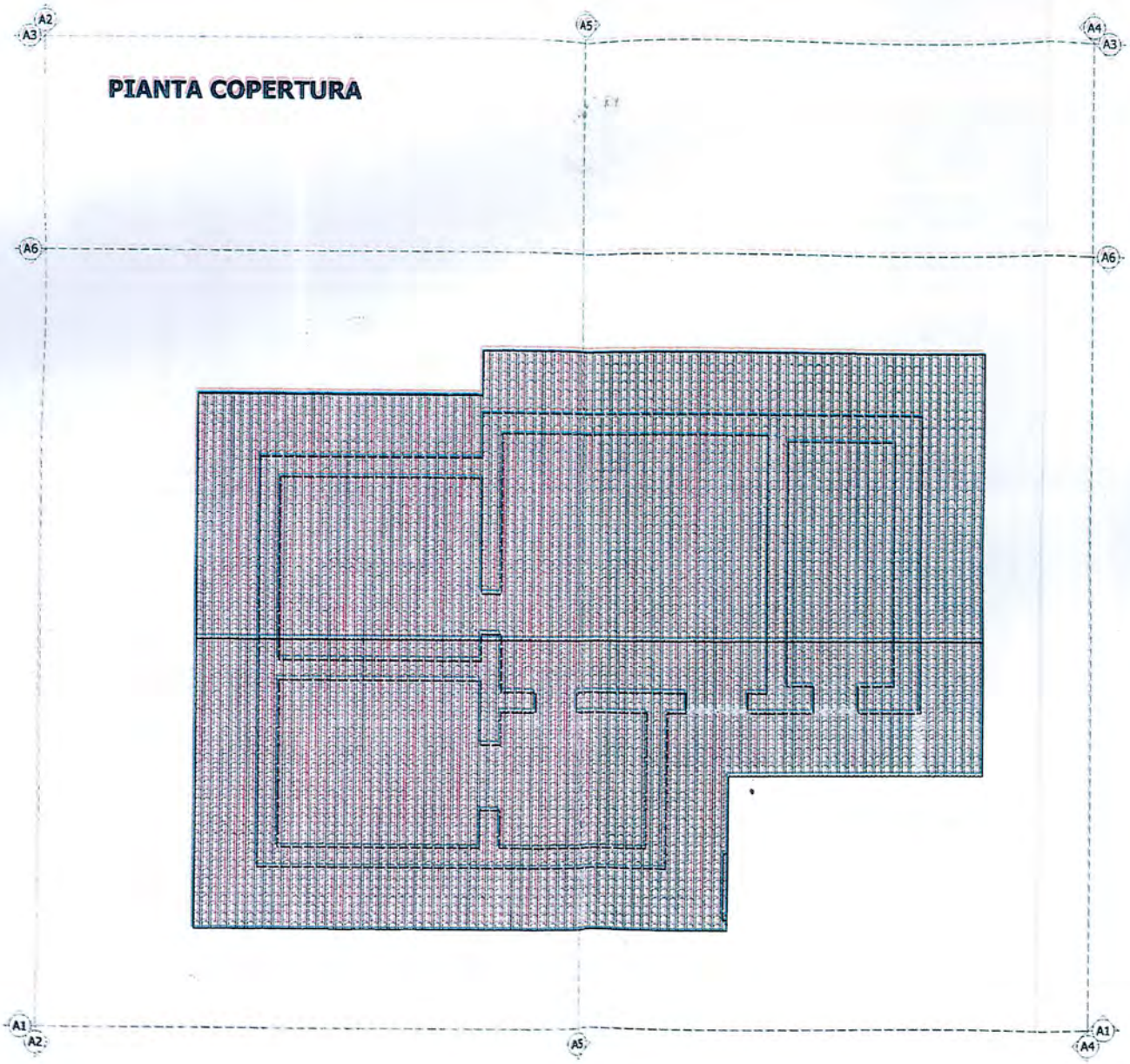

PROSPETTO 01

scala 1 : 100

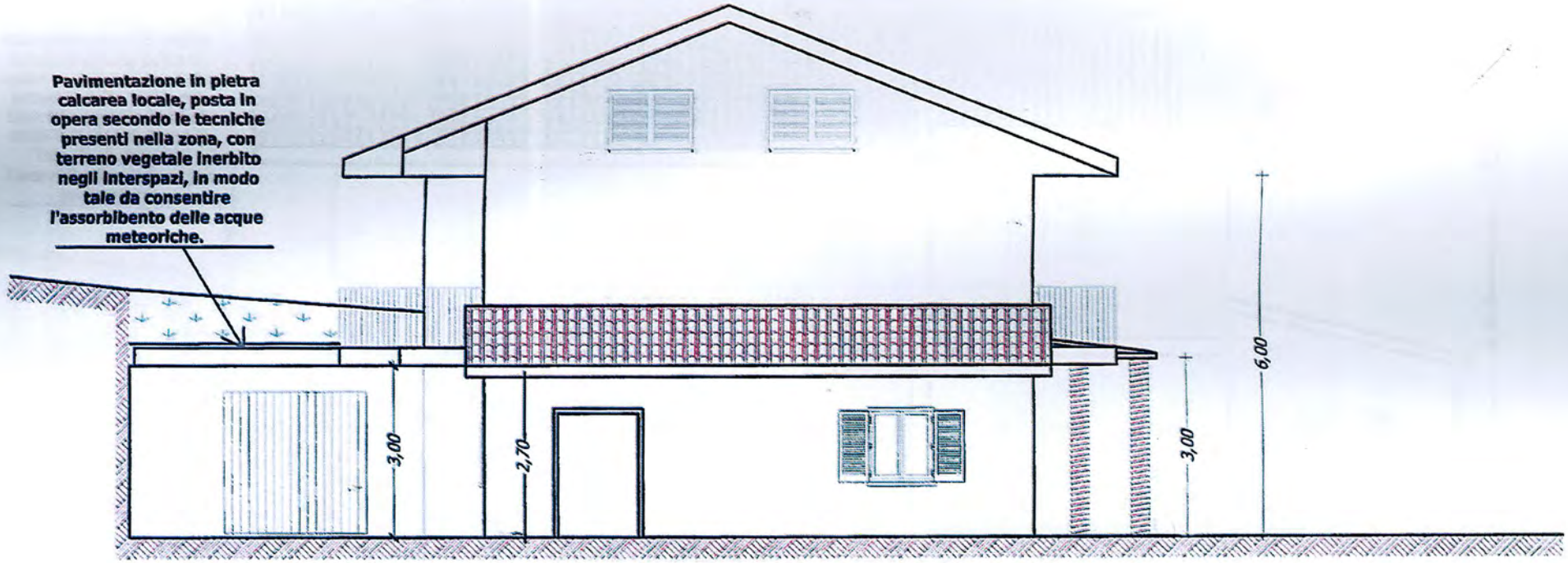

PROSPETTO 02

scala 1 : 100

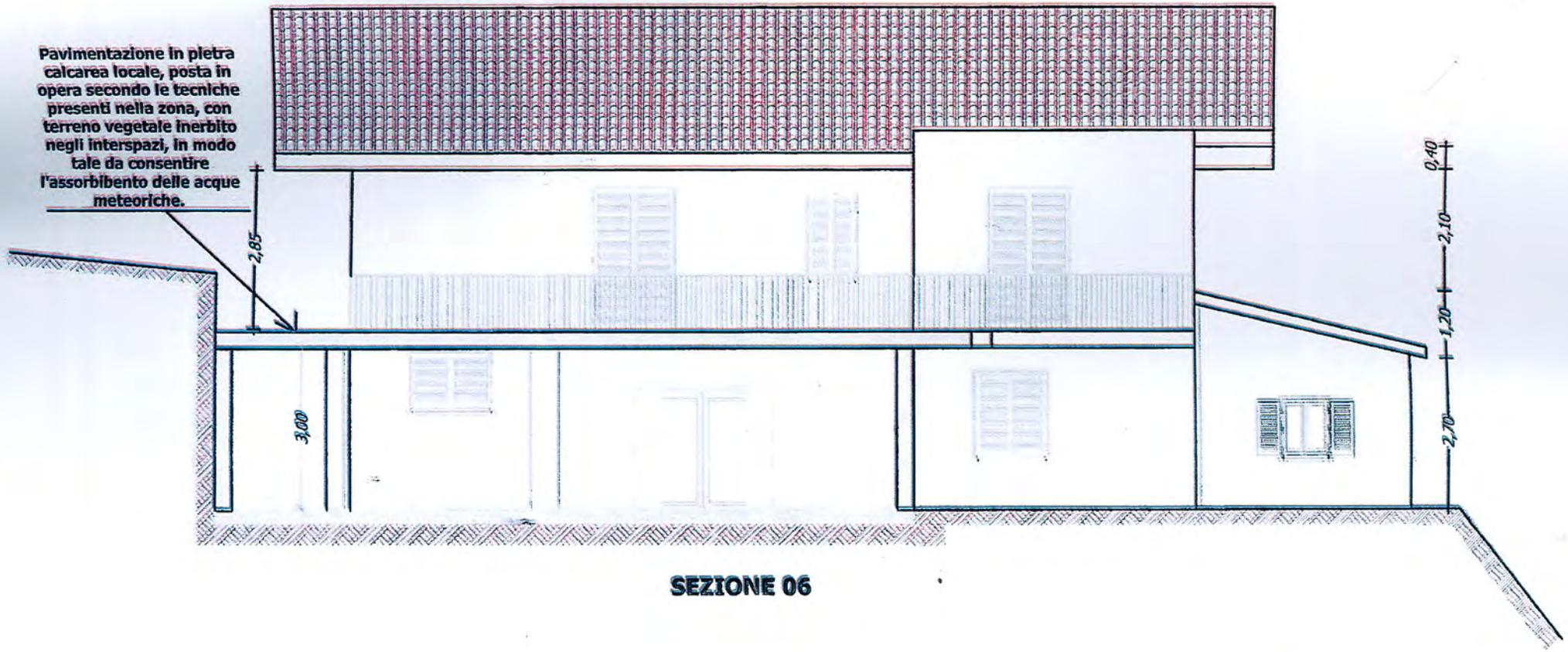

SEZIONE 06

scala 1 : 100

Piante di progetto - scala 1:100

PIANTA PIANO TERRA con gli interventi di progetto
H=280 cm – scala 1:100

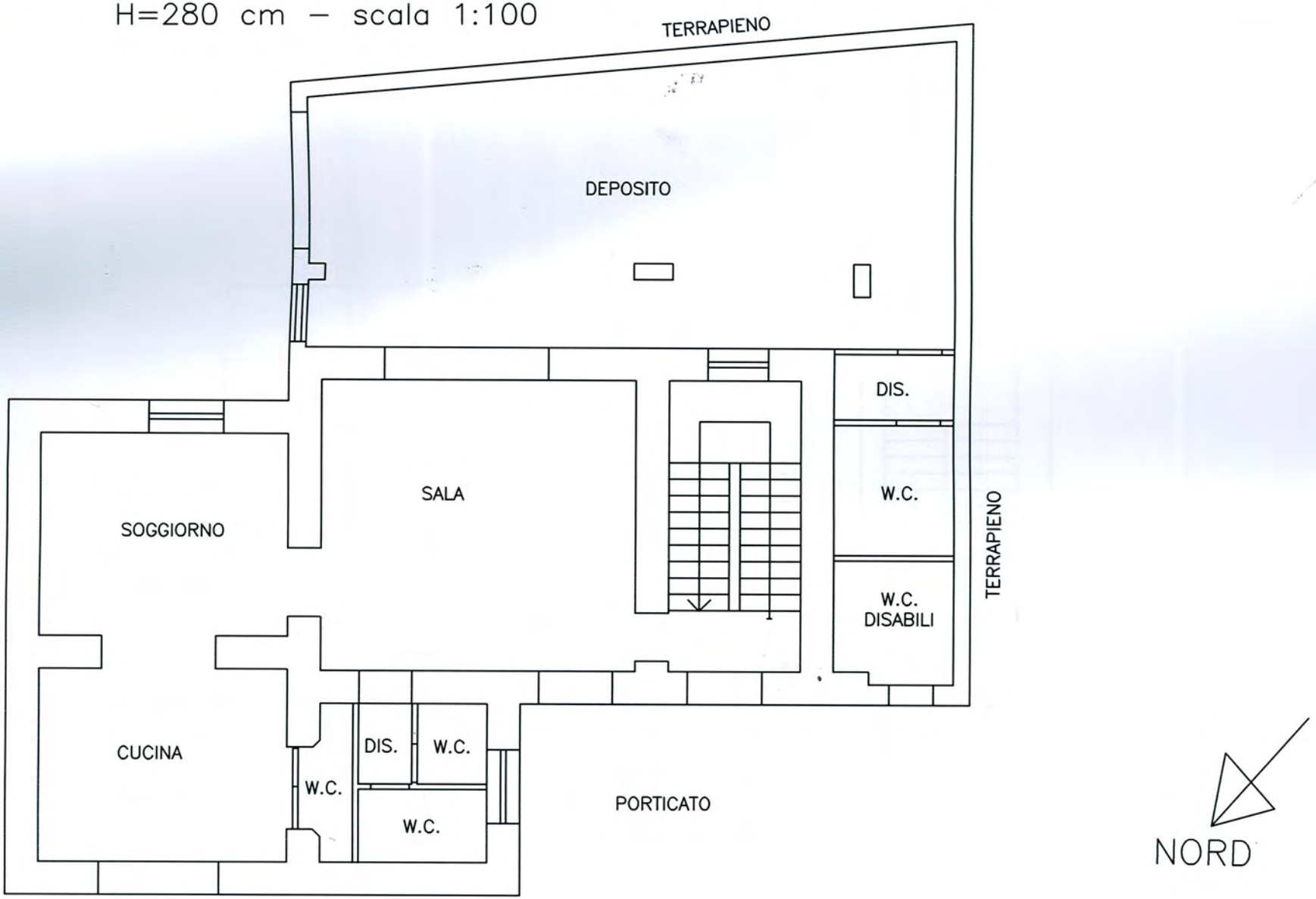

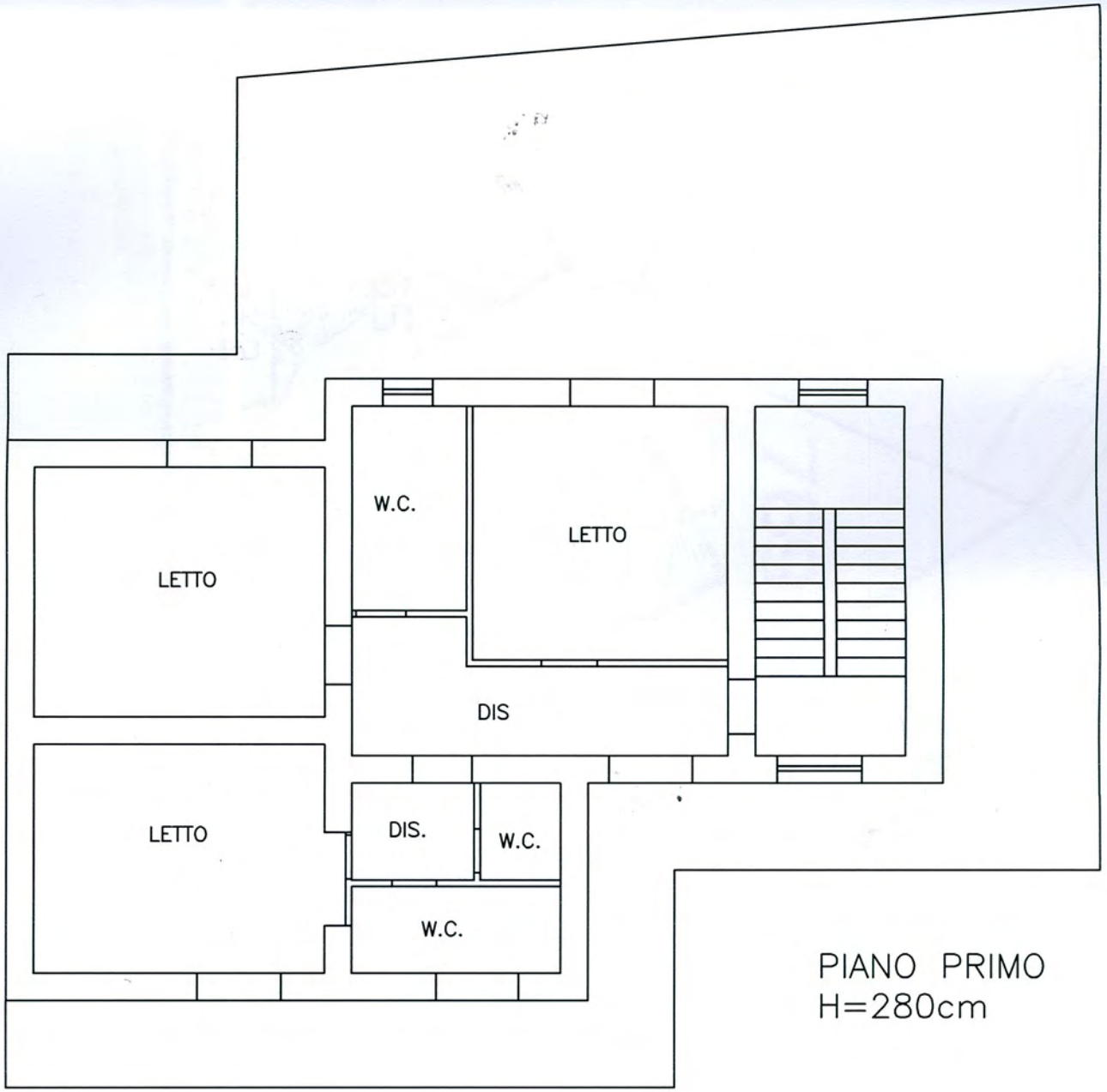

PIANO PRIMO
H=280cm

PLANIMETRIA CATASTALE PARTICOLAREGGIATA
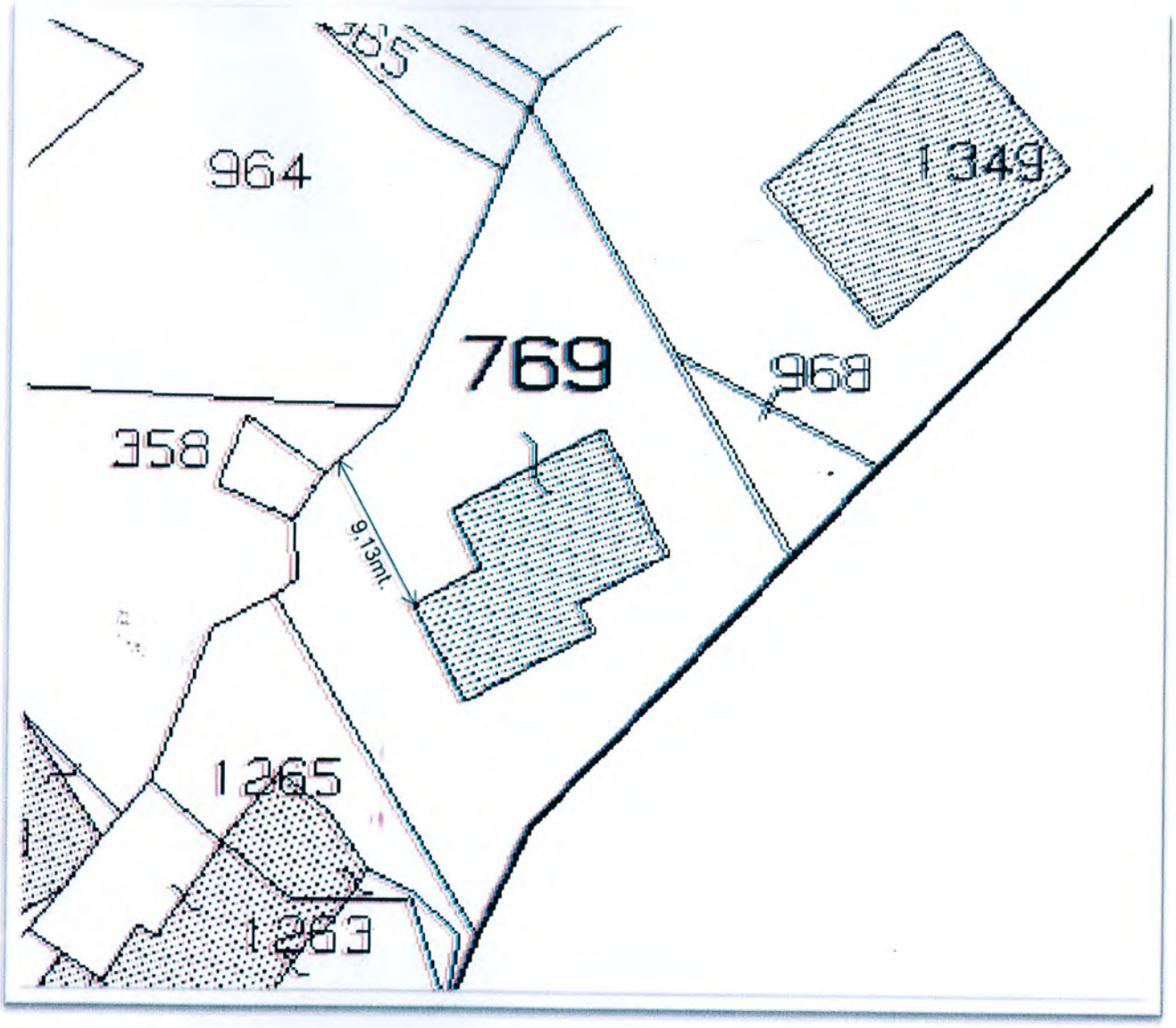
Distanza dal confine per pareti finestrate > di 5mt.