ALLEGATO 1: TITOLO N. 376/A

Legge 219/81

Autorizzazione originaria con stato di fatto ante - intervento

Intervento non realizzato

Progetto integralmente sostituito dal successivo titolo abilitativo

Comune di CAMPOLI DEL MONTE TABURNO

PROVINCIA DI BENEVENTO

N. 376/A Prot. li, 23/10/1987

RILASCIO DI AUTORIZZAZIONE PER LAVORI DI COSTRUZIONE - ~~RIPARAZIONE~~

ASSEGNAZIONE CONTRIBUTI

IL SINDACO

– Vista la domanda del Sig. Caporaso Nicola==========
nato a Campoli del Monte Taburno========== il 19/02/1921==========
residente in Campoli del M.T.======= alla Via Pantanella========== N. ====
codice fiscale CPR NCL 21B19 B542E==========
presentato a quest'Ufficio in data 08/04/1982========== N. 1119 intesa ad ottenere un contributo e l'autorizzazione per eseguire i lavori di ricostruzione - ~~riparazione~~ dell'immobile ad uso di Abitazione e pertinenze agricole==========
composto di piani 3========== vani 4========== utili, accessori 4==========
sito in questo Comune alla Via Pantanella========== N. ====
~~distrutto~~ - danneggiato dal terremoto del 23/11/1980==========

– Considerato che i vigenti piani urbanistici comunali non ostano al rilascio della richiesta autorizzazione;

– Accertato il titolo del richiedente al diritto di quanto richiesto ==========
==========

– Visti gli articoli 9 e seguenti della legge 14 maggio 1981, N. 219:

A S S E G N A

al Sig. Caporaso Nicola nato il 19/02/1921==========
il contributo di ricostruzione - ~~riparazione~~ di L. 117.770.000==========
per l'esecuzione dei lavori descritti in premessa.
==========
==========
==========
==========

AUTORIZZA

i lavori per l'esecuzione delle opere previste nel progetto redatto dal l' Ing. Luigi Caporaso== ==========in data 18/07/1987==========

che si rimette in copia all'interessato debitamente vistato dal sottoscritto Sindaco.

I lavori suddetti dovranno avere inizio entro il giorno =====UN ANNO======ed essere ultimati entro il =======TRE ANNI=====

Contestalmente dispone per l'accreditamento del contributo concesso previo l'Istituto di Credito === Banca del Lavoro e del Piccolo Risparmio di Foglianise==========

ordinativo di pagamento ==========

==========

Il concessionario del contributo effettuerà i prelevamenti in conformità di quanto disposto dal primo comma dell'art. 15 della legge N. 219/81 e cioè:

a) in ragione del 25% dell'importo concesso, all'inizio dei lavori certificato del Sindaco;

b) in ragione dell'ulteriore 60% dell'importo concesso, in base a stato di avanzamento sottoscritto; con responsabilità solidale, dal proprietario, dal direttore dei lavori e dall'impresa, da presentarsi all'Azienda di Credito;

c) in ragione del residuo 15% dell'importo concesso, dopo l'ultimazione dei lavori e l'accertamento della regolare esecuzione degli stessi a cura del Comune.

Il presente provvedimento viene redatto in duplice esemplare, di cui uno viene conservato dal Segretario Comunale, rubricato in ordine alfabetico, dopo l'affissione al pubblico per 10 giorni.

COMUNE DI CAMPOLI DEL MONTE TABURNO ★ BENEVENTO ★

n. 376/a

Pubblicato all'Albo Pretorio del Comune dal 26/10/1987 *al* 10/11/1987

e rubricato il 11/11/1987

li. 11/11/1987

COMUNE DI CAMPOLI DEL MONTE TABURNO ★ BENEVENTO ★

IL SEGRETARIO COMUNALE

li. 7/01/1988

Il Concessionario

ALLEGATO 2: TITOLO 71/88

Legge 219/81

Autorizzazione in variante integralmente sostitutiva del precedente titolo 376/A

Progetto definitivo integralmente realizzato conformemente allo stato di fatto attuale esclusa la porzione di vano scala emergente dalla facciata frontale al piano terra, non realizzata

COMUNE DI CAMPOLI DEL MONTE TABURNO

PROVINCIA DI BENEVENTO

C. A. P. 82030 Tel. 87 30 79

Prot. n° 71/88 Li, 21/04/198

Legge n° 219 del 14/05/1981 e successive modifiche ed integrazioni.

RILASCIO AUTORIZZAZIONE PER I LAVORI

****

AUTORIZZAZIONE VARIANTE AI SOLI FINI URBANISTICI

****

IL SINDACO

Premesso:

-che il Sig. CAPORASO NICOLA==========, nato a Campoli del M.T. il 19/02/1921 e residente Campoli del M.T. alla via Pantanelle=====, n° ======, titolare dell'autorizzazione n° 376/A del 23/10/1987 relativa alla ricostruzione del fabbricato rurale======= sito alla via Pantanelle ==== di questo Comune e benificiario del contributo di £. 117.770.000 (diconsi lire centodiciasettemilioni 770.000========), determinato dalla Commissione Tecnica Comunale di cui all'art.14 della suddetta legge, nella seduta del 15/10/1987 con verbale n° ==4===;

-che lo stesso in data 18/03/1988 ha prodotto nuova istanza assunta al protocollo di questo Comune al n° 962==, atta ad ottenere l'approvazione della variante del progetto originario ai soli fini urbanistici;

-accertato il titolo del richiedente al diritto di quanto richiesto;

-sentito la Commissione Tecnica Comunale che ha espresso parere favorevole nella seduta del 29/03/1988 n° ==21====:

a u t o r i z z a

· lavori per l'esecuzione delle opere previste nel progetto di variante redatto dal l'Ing. Caporaso luigi==========in data 18/03/1988 che si rimette in copia all'interessato debitamente vistato dal sottoscrit= to Sindaco.

anno parte integrante della presente tutte le prescrizioni ed adempimenti revisti nel Decreto originario.

Il presente provvedimento viene redatto in duplice esemplare, di cui uno viene conservato dal Segretario Comunale, rubricato in ordine al= fabetico, dopo l'affissione al pubblico per 10 giorni.

COMUNE DI CAMPOLI DEL MONTE TAURANO * BENEVENTO *

IL SINDACO

Pubblicato all'Albo Pretorio del Comune suddetto dal 27/4/88 al 7/5/88 e rubricato 10-05-1988

Li, 10-5-88

IL SEGRETARIO

Li, 27/05/88

IL CONCESSIONARIO

Caporaso Nicola

225

RELATA DI NOTIFICA

Certifico di avere notificato oggi Ventisette Maggio 1988 copia della presente, rimettendola a mani di Caporaso Nicola estro nicolesi

Il Messo Comunale

ALLEGATO 4

PERIZIA "DANNO -SISMA" DEFINITIVA

PROGETTO REALIZZATO

ORIGINALE

1

STUDIO TECNICO

Dott. Ing. Luigi Caporaso

CAMPOLI M.T. Tel. 873121

C O M U N E D I :

CAMPOLI M.T.

D I T T A : CAPORASO NICOLA -19-02-1921

L E G G E 1 4 - 5 - 1 9 8 1 N° 2 1 9

e successive modifiche ed integrazioni

P R O G E T T O

Ricostruzione di un fabbricato rurale
SITO IN c/da Pantanelle
ADIBITO A civile abitazioni e pertinenze agricole

PERIZIA VARIATIVA

IL PROGETTISTA
Dott. Ing. Luigi Caporaso

DOTT. ING. CAPORASO LUIGI
ALBO INGEGNERI Provincia di BENEVENTO n. 317
CAMPOLI M.T. (BN)

Dichiarazione di connessione danno-sisma./ Planimetria dello stato di fatto preesistente al sisma./ Progetto esecutivo dei lavori./ Computo metrico estimativo./ Limite di convenienza economica./ Determinazione del contributo.

I. PARTE da pag 1 a 120

Il Presidente

I Componenti

29 MAR. 1988

INQUADRAMENTO URBANISTICO

LA VOLUMETRIA REALIZZABILE IN DEROGA AGLI INDICI DI FABBRICABILITA' DEGLI STRUMENTI URBANISTICI, AI SENSI DELL'ART. 56 DELLA LEGGE 14/5/1981 N.ro 219, E' PARI ALLA VOLUMETRIA ESISTENTE AUMENTATA DEL 30 %.
NEL CASO IN ESAME LA VOLUMETRIA ESISTENTE E' PARI A:

vano 1: 5.49 x 6.74 x 3.00 = mc 111.01

vano 2: 4.65 x 3.89 x 2.70 = mc 48.84

vano 5: 3.89 x 5.35 x 3.20 = mc 66.60 .

vano 4: (2.96 x 3.6 + 4.72 x 3.65) x 3.2 = mc 89.23 .

vano 10: 1.74 x 3.13 x 2.70 = mc 14.70

vani 7,8,9: 8.83 x 7.74 x 3.20 = mc 218.70;

TOTALE mc 549.08;

LA VOLUMETRIA REALIZZABILE E' DI:

mc 549.08 x 1.30 = mc 713.80.

LA VOLUMETRIA DEL NUOVO IMMOBILE E' PARI A:

(14.20 x 8.30 - 2.80 x 2.40) x 3.20 + 6.90 x 14.20 x 3.20 =

mc 669.18.

ED E' CONTENUTA NEI LIMITI DI QUELLA ASSENTIBILE.

* DISTINTA DELLE SUPERFICI ESISTENTI *

Proprietario: CAPORASO NICOLA (19-02-1921)

Vano n'	Destinazione d' uso	Dimensioni metri	Superfici in mq.				
			S.U.	S.N.R.	S.A.A.	A.	S.A.P.
1	Stalla	4.09 x 5.34			21.84		
2	Stalla	3.95 x 3.14			12.40		
5	Dep.attr.agr.	3.95 x 3.14			12.40		
6	Balcone	0.20 x 1.40		0.28			
7	Balcone	0.20 x 1.50		0.30			
4	Cucina	2.56 x 2.26	5.79				
4		2.95 x 4.02	11.86				
7	Camera	4.20 x 3.20	13.44				
8	Camera	4.28 x 3.24	13.87				
9	Soggiorno	3.16 x 2.26	7.14				
9		3.42 x 4.22	14.43				
10	Bagno	2.93 x 1.64	4.81				
TOTALI			71.33	0.58	46.65	0.00	0.00

S. U. = Superficie utile abitabile.
S.N.R. = Superficie per servizi ed accessori.
S.A.A. = Superficie per lo svolgimento dell'attivita' agricola.
A. = Autorimessa.
S.A.P. = Superficie per attivita' produttiva.

* DISTINTA DELLE SUPERFICI DI PROGETTO *

Proprietario: Caporaso Nicola (19-02-1921)

Vano n°	Destinazione d' uso	Dimensioni metri	Superfici in mq.				
			S.U.	S.N.R.	S.A.A.	A.	S.A.C.
2	Cucina	3.90 x 2.70	10.53				
3	Disimpegno	1.30 x 3.60	4.68				
4	Camera	3.50 x 3.90	13.65				
4		0.50 x 2.50	1.25				
10	Cucina	3.90 x 2.70	10.53				
11	Disimpegno	1.30 x 3.60	4.68				
12	Camera	3.50 x 3.90	13.65				
12		0.50 x 2.50	1.25				
5-13	Bagni 2x	2.20 x 2.50	11,00				
1	Porticato	1.40 x 5.60		7.84			
14	Porticato	1.40 x 5.60		7.84			
8	Cantinola	2.70 x 5.30		14.31			
6	Autorimessa	5.30 x 3.40				18.02	
7	Dep.attr.agr.	5.30 x 4.20			22,26		
9	Cantina	5.30 x 4.90			25.97		
TOTALI			71,22	29.99	48,23	18.02	0.00

S. U. = Superficie utile abitabile.
S.N.R. = Superficie per servizi ed accessori.
S.A.A. = Superficie per lo svolgimento dell'attivita' agricola.
A. = Autorimessa.
S.A.C. = Superficie per attivita' commerciale.

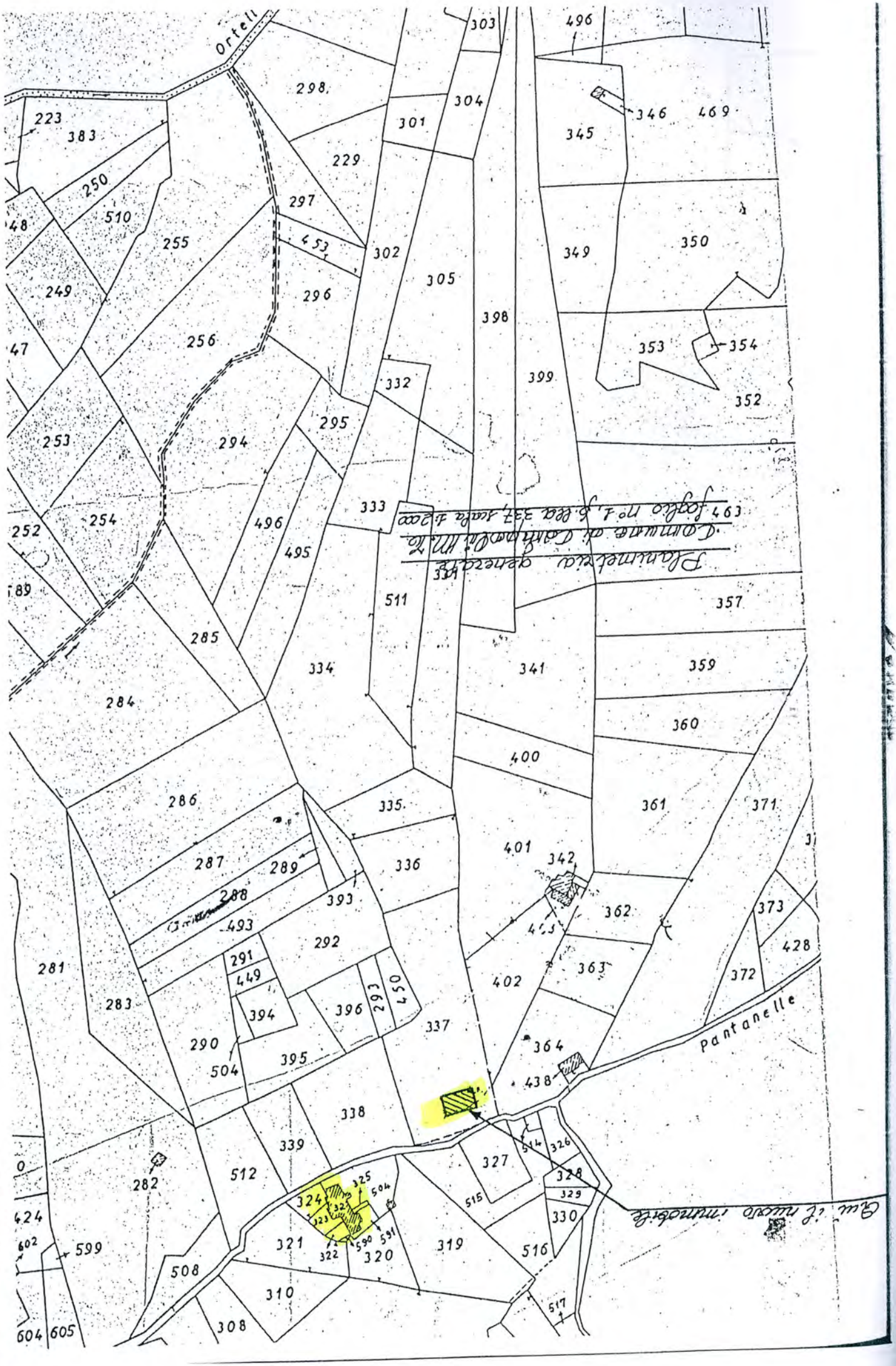
Ortell
Pantanelle
Fiume di Mezzo
223
383
250
510
255
249
256
253
254
252
189
47
48
297
298
229
453
296
301
302
304
303
496
305
398
399
332
295
294
333
496
495
511
285
284
286
287
289
288
493
281
283
291
449
394
292
393
396
262
450
290
504
395
335
336
337
338
339
512
282
324
325
323
322
504
590
591
320
321
319
327
514
326
328
329
330
515
516
517
508
310
308
604
605
599
602
424
0
346
469
345
349
350
353
354
352
357
359
360
361
371
341
400
401
342
362
363
402
364
438
373
428
372
334
511
331
Planimetria generale
Comune di Carbonera (TV)
Foglio n° 1, Sez. 337, scala 1:2000

Qui il nuovo immobile
16.60
16.50
8.00
8.00
7.50
7.50
517
310
516
319
320
322
321
590
591
330
323
324
329
515
504
325
328
327
326
514
339
338
438
395
364
337
396
394
293
450
402
363
449
292
91
93
362
393
289
342
336
401
361
335
400
Planimetria particolareggiata
foglio n° 1, p.lla 337,
scala 1:1000

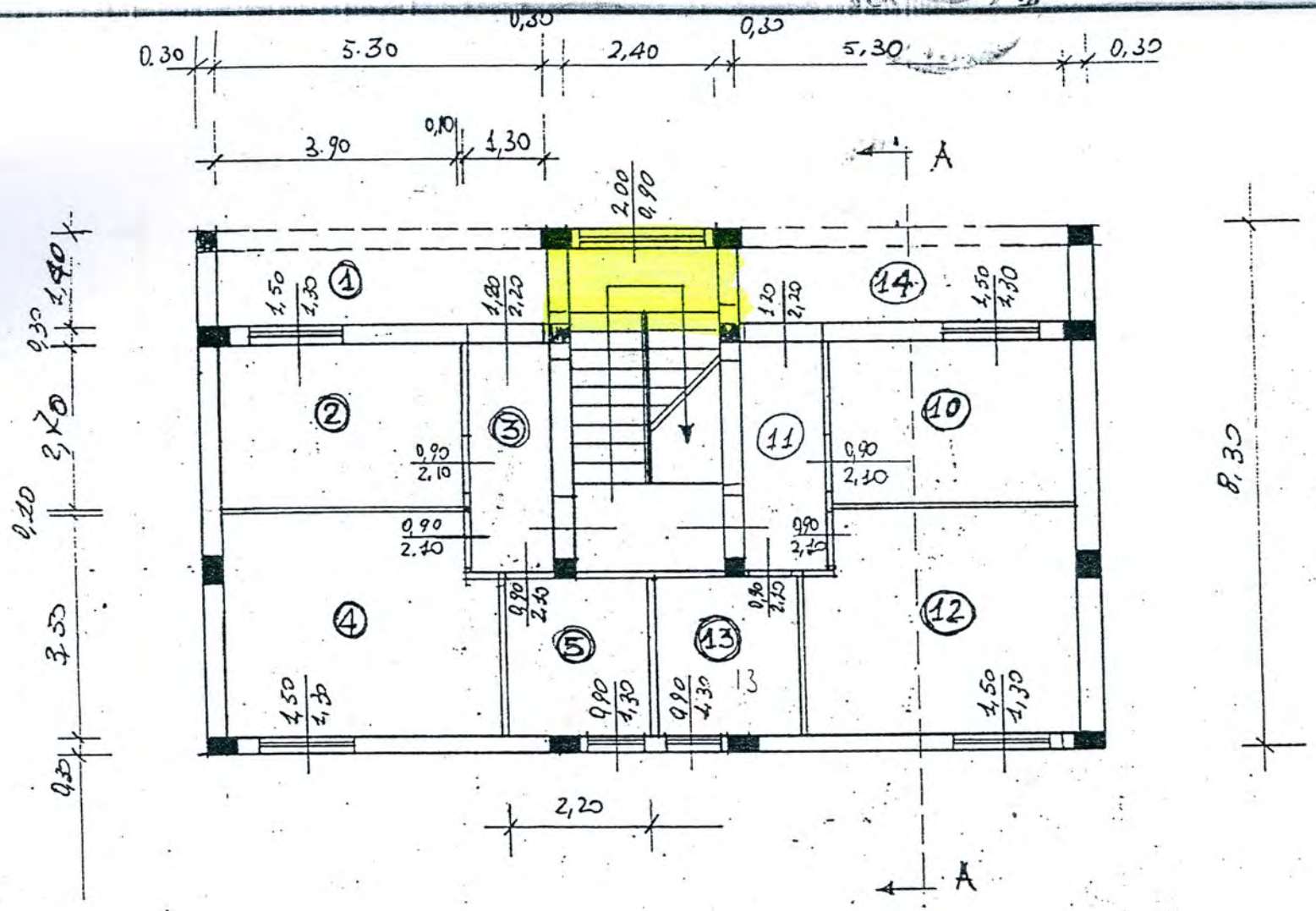

PIANTA PRIMO PIANO SCALA 1:100

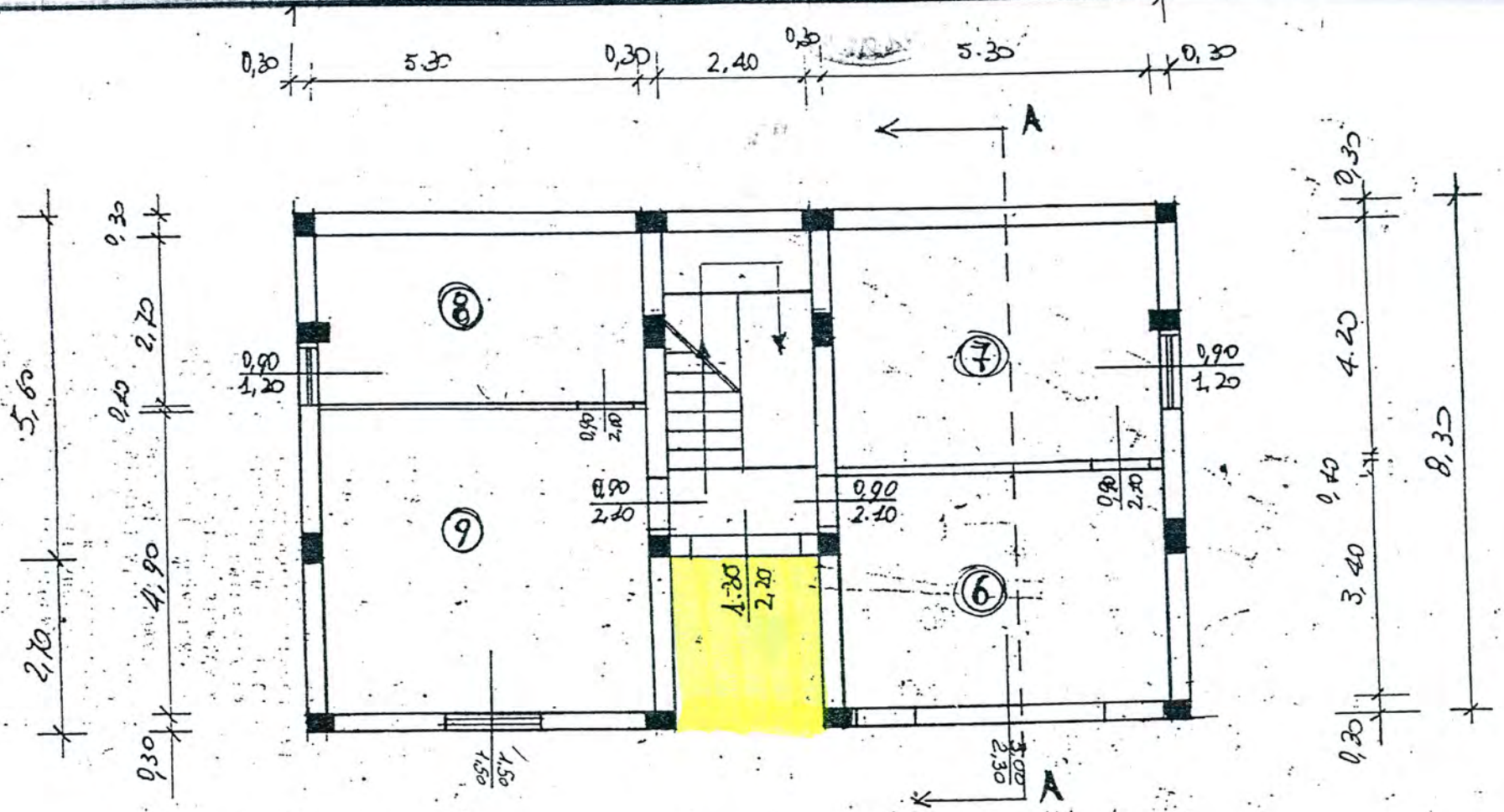

PIANTA SEMINTERRATO SCALA 1:100

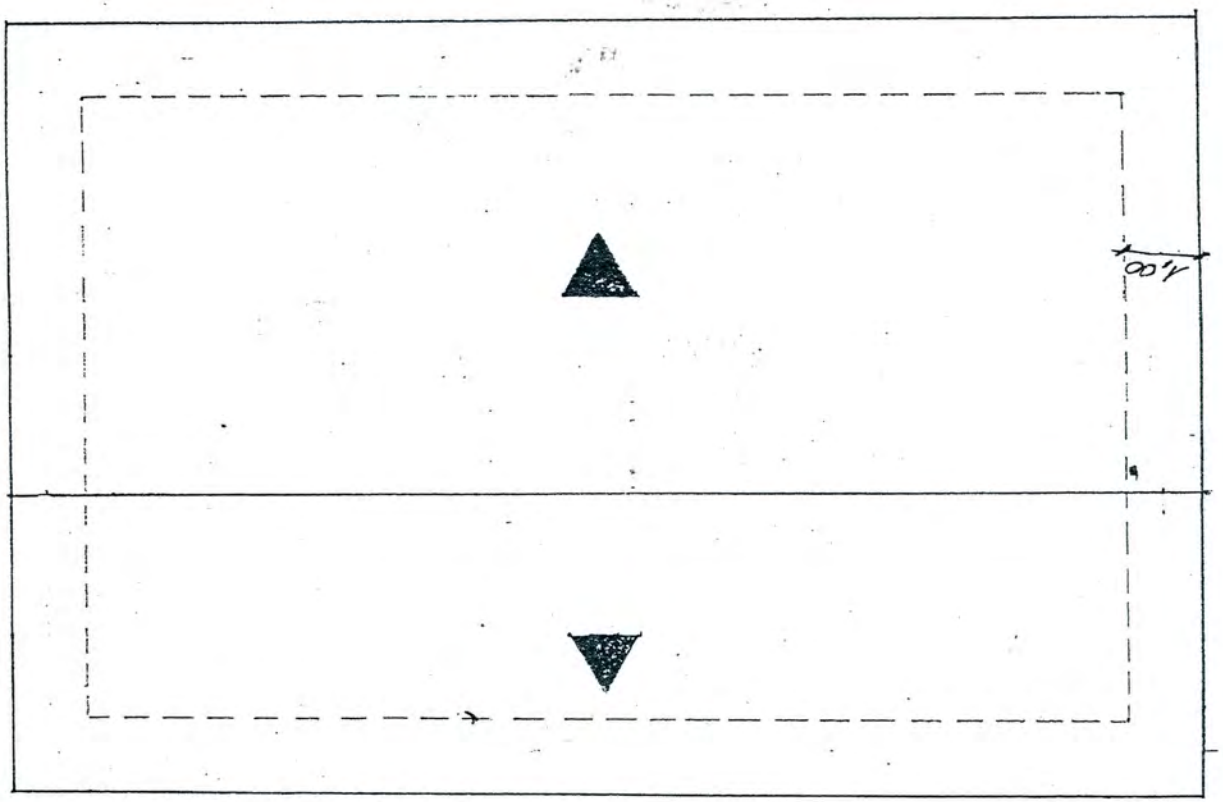

PIANTA COPERTURE

SEZIONE A-A SCALA 1:100

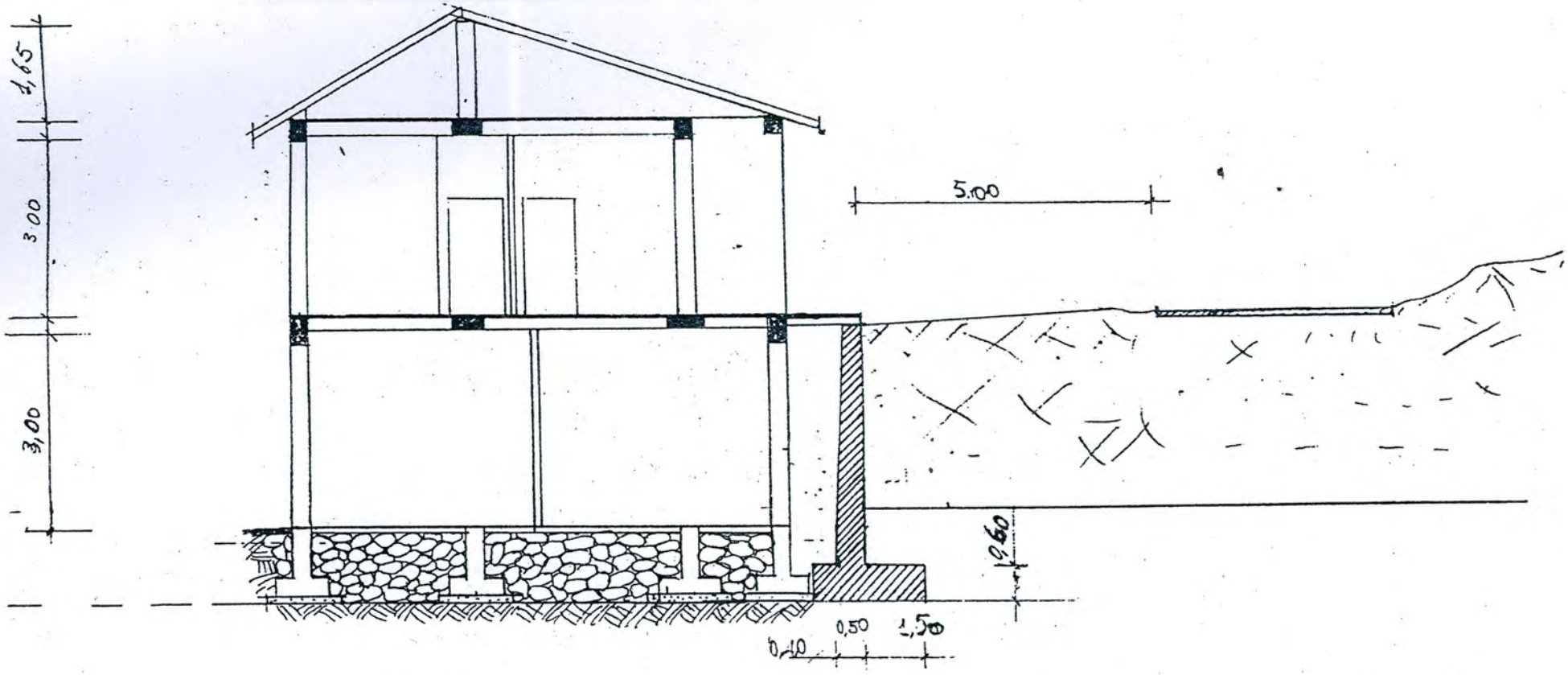

PROSPETTO - SCALA 1:100



ALLEGATO N. 6

ALTEZZA FABBRICATO DA PIANO DI CALPESTIO A LIVELLO
DI ESTRADOSSO SOLAIO DI SOTTOTETTO