Comune di
CAMPOLI M.T
Provincia di Benevento

OGGETTO : INTERVENTO LOCALE per la modifica di alcuni vuoti interni e per la riorganizzazione dei servizi igienici, relativo ad un fabbricato sito alla località ROGGIANO.

COMMITTENTE: Ciotta Gerardina

ALLEGATO UNICO: PROGETTO ARCHITETTONICO (Relazione Tecnica - Grafici dello stato di fatto e di progetto - Planimetria Catastale).

Febbraio 2020

Il Progettista e DD.L.
(ing. Mario Saverio Orlacchio)

Dott. Ing. Orlacchio Mario Saverio
ALBO INGEGNERI Provincia di BENEVENTO n. 680
Campoli M.T. (BN)

COMUNE DI CAMPOLI M.T.

(provincia di BENEVENTO)

OGGETTO: Progetto per la realizzazione di interventi locali (*opere interne interessanti anche la struttura dell'immobile*) e per la nuova organizzazione dei servizi igienici inerenti un fabbricato adibito ad attività ricettiva di ristorazione (*Turismo Rurale*) alla località ***"Roggiano"***.

COMMITTENTE: *CIOTTA Gerardina*

RELAZIONE TECNICA

Premessa

La committente, Ciotta Gerardina, nella sua qualità di affittuaria dell'immobile opportunamente autorizzata dal proprietario (Cfr. dichiarazione di autorizzazione), ha conferito incarico allo scrivente ing. Mario Saverio Orlacchio, nato a Campoli M.T. (Bn), il 21/11/1960, ivi residente alla via San Nicola Vecchio, 47, iscritto all'Ordine degli Ingegneri di Benevento con n. 680, di redigere il presente progetto per la realizzazione di alcune opere interne puntuali e per la riorganizzazione dei servizi igienici inerenti un fabbricato adibito a turismo rurale alla località ***"Roggiano"***.

- **Individuazione dell'area oggetto di intervento ed analisi dei vincoli.**

L'intervento in parola interessa un fabbricato identificato in mappa con la p.lla n.1032 sub.3 del foglio n. 1 di Campoli M.T.; compreso in zona *"Agricola E"* del vigente P.R.G. ed in zona RUA del P.T.P..

L'area risulta esterna a quella classificata come a rischio frana sull'apposita carta redatta dall'Autorità di Bacino dei Fiumi Liri-Garigliano e Volturno, non è soggetta a vincolo idrogeologico e risulta esterna alla perimetrazione del Parco del Taburno Camposauro.

- **Precedenti autorizzazioni.**

Il fabbricato adibito a turismo rurale (*affittacamere con piccola ristorazione*) è stato realizzato con il permesso di costruire n.14 del 22/03/2004 rilasciato dal comune di Campoli M.T. (Bn) con il quale si autorizzava la ristrutturazione e la riqualificazione funzionale

di un fabbricato rurale da adibire ad attività di recezione alberghiera turismo rurale. Sono stati inoltre rilasciati dal Comune di Campoli M.T., PDC a sanatoria per modifiche alle facciate esterne n. 8 del 14/04/2008 e permesso a costruire n.10 del 10/06/2008 per l'ampliamento dell'immobile esistente. Durante l'esecuzione delle opere la titolare dei PDC (*affittuaria Ciotta Gerardina*) realizzava varie difformità rispetto a quanto autorizzato; in riferimento alle stesse il Comune di Campoli M.T. con propria ordinanza di demolizione n.1 del 17/09/2013 di prot. n.2132 e successivo atto integrativo n.1 del 23/06/2014 di prot. n. 1700 intimava la demolizione di tutte le opere abusive e quindi di riportare il fabbricato nelle condizioni di conformità rispetto al progetto approvato dallo stesso Ente. L'affittuaria dell'immobile, Ciotta Gerardina presentava al Comune varie istanze a sanatoria di cui l'ultima è la CILA di prot. n.3410 del 12/11/2019 sulla quale si sono espressi positivamente sia il Responsabile del Procedimento Paesaggistico ing. Loia Papa Angelo *(con nota di prot. n.3888 del 20/12/2019)* che il Responsabile del Settore Tecnico ing. Caporaso Giuseppe il quale, con propria Determina di prot. n. 142 del 15/01/2020 ha archiviato il procedimento in quanto la ditta committente ha ottemperato in parte all'ordinanza di demolizione di cui innanzi mentre per la parte residuale in difformità ha provveduto alla relativa sanatoria.

- **Opere di progetto.**

Il presente progetto prevede l'ampliamento di alcuni vuoti esistenti e l'apertura di alcuni nuovi vuoti nella muratura portante di spina. Tali opere puntuali, si rendono necessarie per consentire una maggiore fruibilità degli ambienti e migliorare qualitativamente il servizio offerto incentivando la richiesta esterna in conformità alle disposizioni generali per il turismo rurale. Si prevede inoltre, la realizzazione di nuove tramezzature interne per una diversa distribuzione dei servizi igienici senza apportare variazione della destinazione d'uso e l'apertura di due piccole finestre per consentirne l'areazione.

Si eseguiranno altresì, le conseguenziali opere di ripristino e nuove opere es. pavimenti, rappezzi di intonaco tinteggiatura ecc.

Alcune delle opere di progetto, poiché interessano, anche se parzialmente, la struttura del fabbricato, sono state opportunamente calcolate e verificate in conformità alla vigente normativa. Per quanto riguarda i scarichi provenienti dai servizi igienici, si precisa che l'immobile risulta già dotato di una fossa biologica del tipo "imhoff" di adeguata capacità che periodicamente viene svuotata da ditta specializzata ed autorizzata per tale operazione.

- **Inquadramento urbanistico.**

Non si prevede la realizzazione di nuove superfici coperte o volumi, pertanto, non risulta necessario verificare alcun parametro urbanistico.

- **Verifica di compatibilità ambientale al P.T.P..**

Le opere di progetto non modificano minimamente l'aspetto esteriore dell'immobile né mutano la destinazione d'uso, pertanto risultano sono conformi a quanto sancito dalle norme di carattere generale ed a quelle specifiche per la zona R.U.A. del P.T.P.. Per quanto riguarda l'apertura di due piccole finestre necessarie per l'aerazione dei servizi igienici, si evidenzia che tale opera rientra tra gli interventi esclusi da autorizzazione paesaggistica così come riportato nella tabella A allegata al DPR 31/2017.

- **Conclusioni.**

Alla luce di quanto innanzi esposto, emerge chiaramente che l'intervento proposto è compatibile sia dal punto di vista ambientale che urbanistico, in quanto non si alterano le caratteristiche dello stato dei luoghi, ma si interverrà con minime variazioni sul fabbricato senza interferire con l'ambiente circostante.

Per ogni altro si rinvia agli elaborati grafici.

Tanto dovevasi.

Il progettista
(ing. Mario Saverio Orlacchio)

Dott. Ing. Orlacchio Mario Saverio
ALBO INGEGNERI Provincia di BENEVENTO n. 680
Campoli M.T. (BN)

PIANO TERRA (SCIA prot. n.1498 del 18/05/2018)

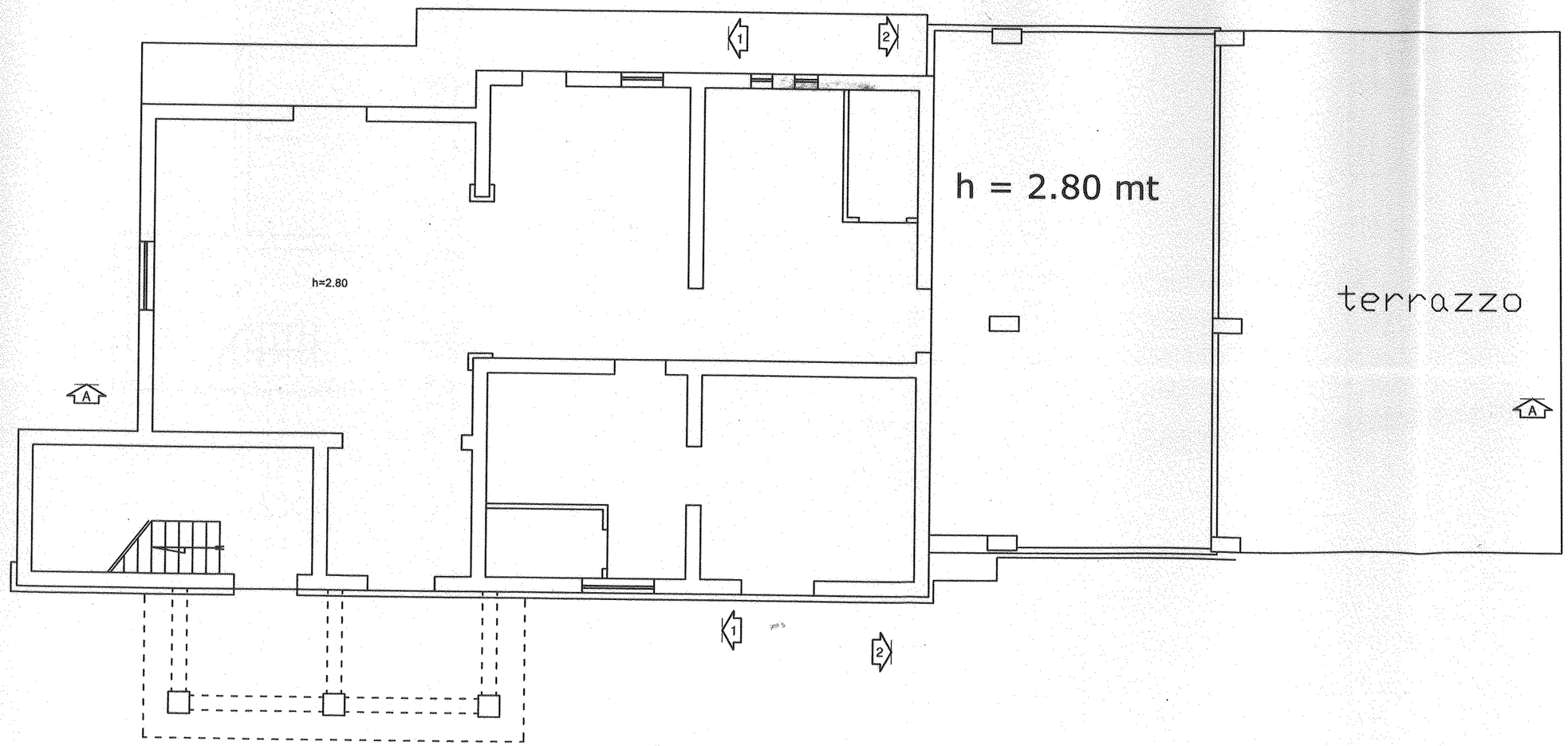

SCALA 1:100

PIANO TERRA (di progetto)

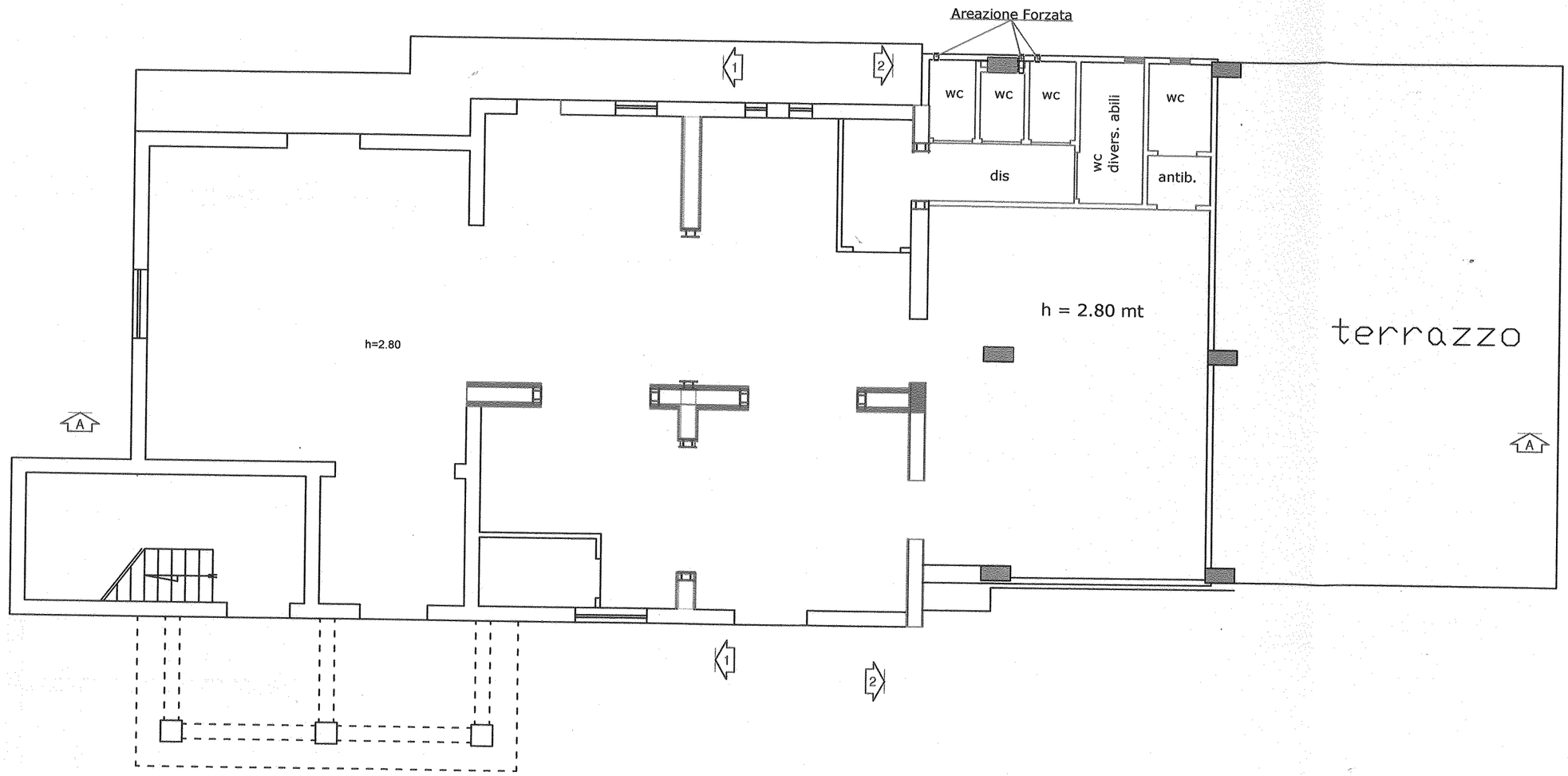

LEGENDA OPERE DI PROGETTO

cerchiatura
(con struttura metallica e rinforzo parete)

nuove tramezzature interne

SCALA 1:100

SEZIONE A-A

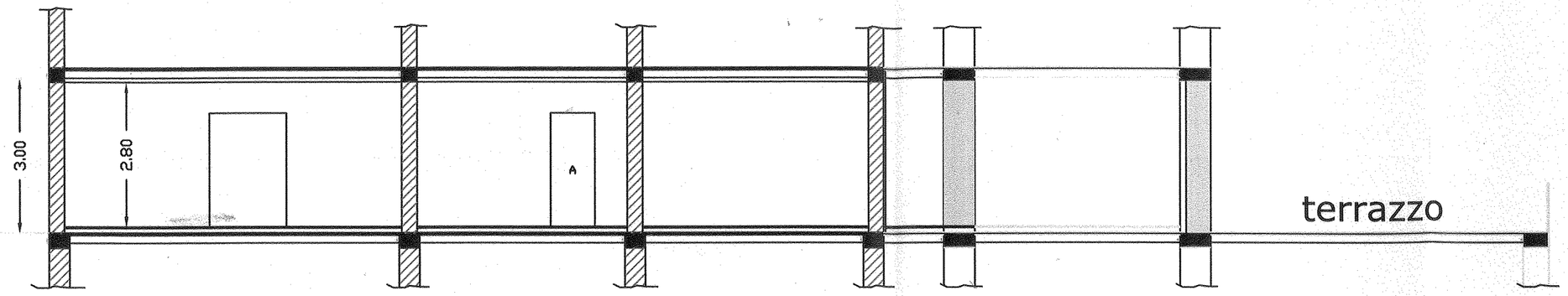

Ante-operam

SEZIONE A-A

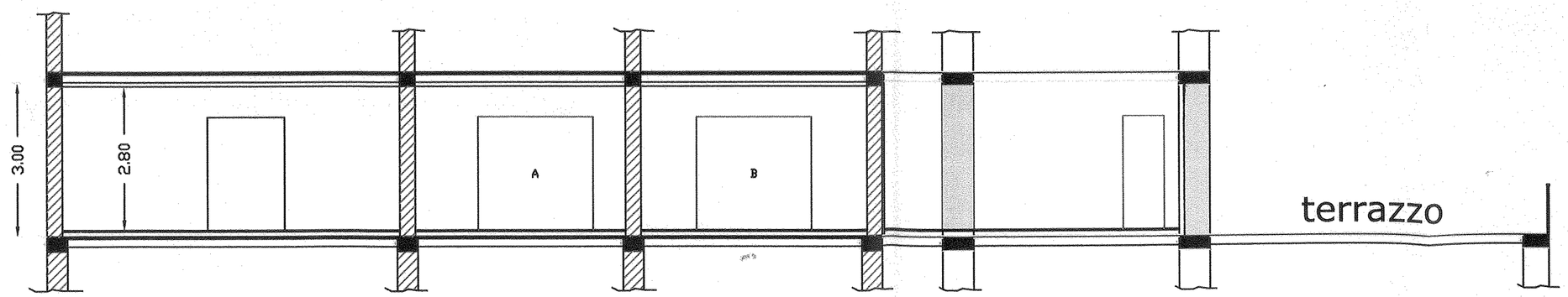

Post-operam

SCALA 1:100

SEZIONE 1-1

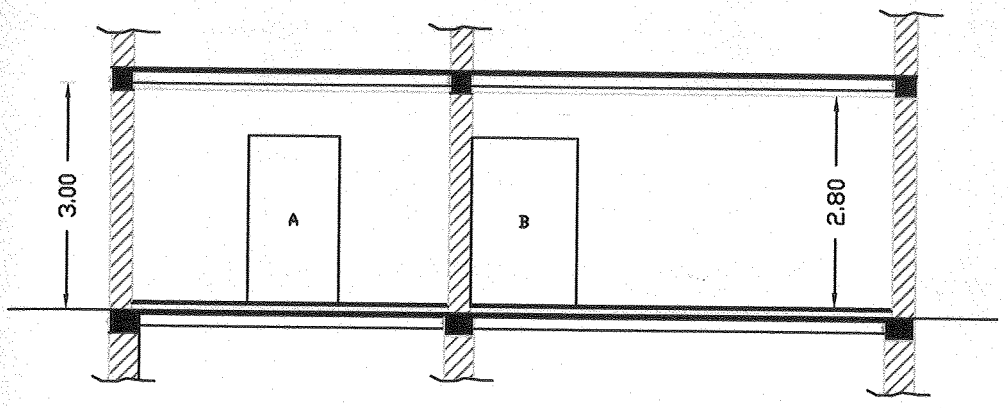

Ante-operam

SEZIONE 1-1

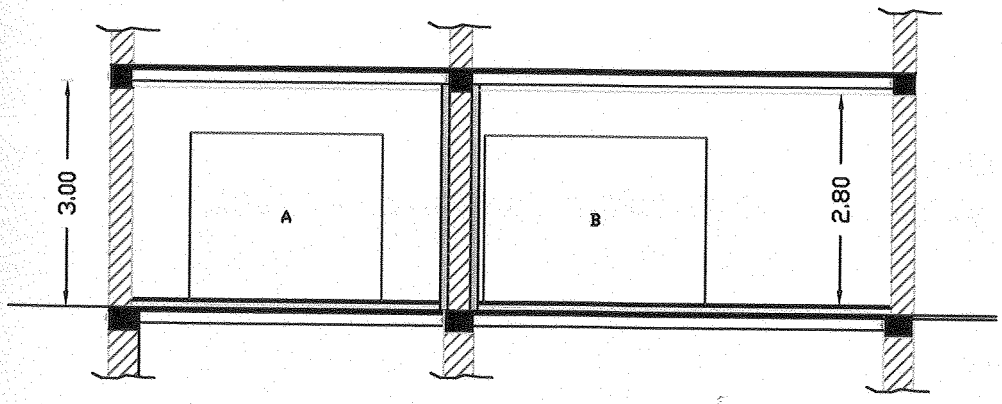

Post-operam

SCALA 1:100

SEZIONE 2-2

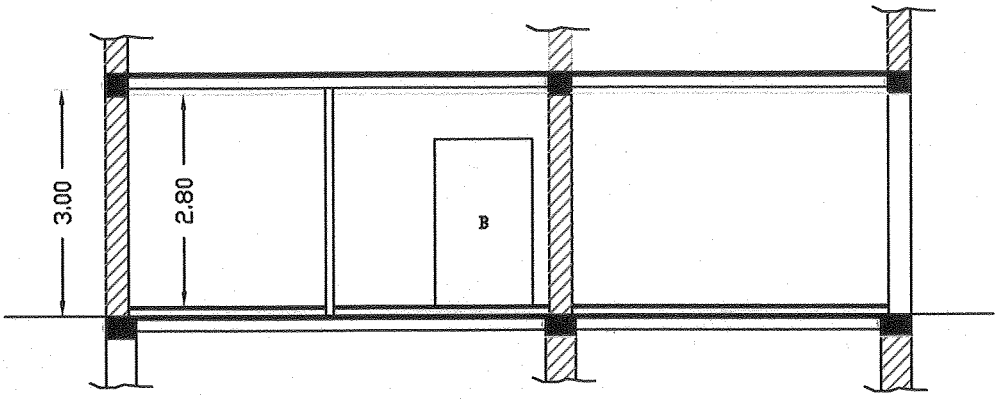

Ante-operam

SEZIONE 2-2

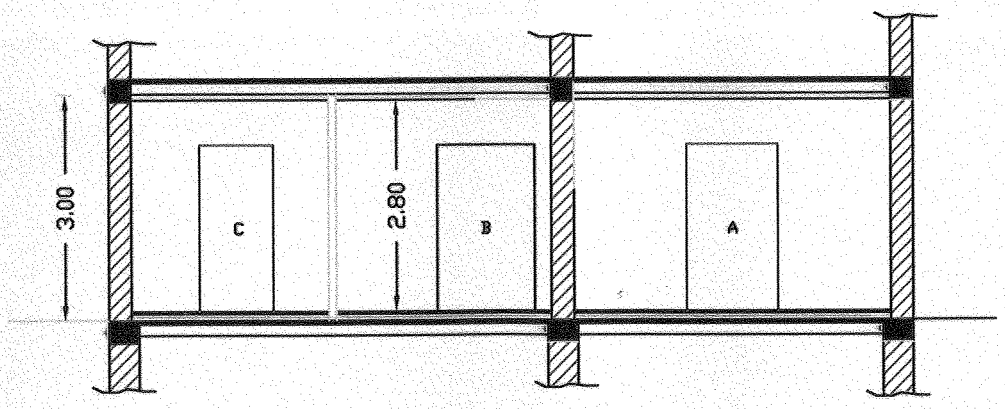

Post-operam

SCALA 1:100

Ufficio Provinciale di BENEVENTO - Direttore: ALDO DELLA SELVA

Per Visura

29-Feb-2012 15:38
Prot. n. T334615/2012

Scala originale: 1:2000
Dimensione cornice: 776.000 x 552.000 metri

Comune: CAMPOLI D MONTE TABURNO
Foglio: 1

Particella: 590